文化传承视角下老城街巷餐饮空间布局研究
——以广州为例[1]

摘要：广州餐饮文化在全国具有独特地位，尤其老城区的街巷餐饮空间更具地方特色和烟火气，因此深度解析广州老城街巷餐饮空间对文化传承和保护具有重要意义。基于 ArcGIS 平台，对美团餐饮店数据进行核密度分析，构建广州老城街巷餐饮空间综合评价体系，从街巷尺度对广州老城区餐饮空间分布进行解析，研究发现：①广州老城街巷餐饮空间存在一定的区域聚集性与区别于中心城区的特征；②广州老城街巷沿街老字号分布较广，老城区内各个区域均有所分布；③广州老城区各高水平聚集餐饮空间分布呈现出东西向轴线分布，且主要围绕重要商圈、旅游景点和核心交通节点形成集聚分布。基于分析本研究提出点-线-面三个层次的空间规划策略，以期为政府规划部门进行城市餐饮空间的布局与规划提供建议，挖掘与弘扬广州老城独特的餐饮地域文化，促进广州地方特色餐饮文化传承与老城区高质量发展。

关键词：文化传承；广州老城区；街巷尺度；餐饮空间；美团数据

0 引言

餐饮业作为城市服务行业的重要组成部分之一，其商户数量与空间分布能够在一定程度上反映一个地区的经济文化发展水平。广州作为国务院公布的全国第一批历史文化名城之一，拥有 2200 多年深厚的历史积淀，其“食在广州”的餐饮文化在全国具有独特地位。而广州老城区传统街巷保留较完整的空间格局，承载城市历史文脉和市民集体记忆，是体现广州餐饮文化特色和传统餐饮空间风貌的最佳空间载体。结合广州地域餐饮文化特征，从街巷尺度对广州老城区的餐饮空间布局进行分析与评价，对指导广州城市规划建设与餐饮空间选址具有重要意义[1]，有助于通过餐饮空间对逐渐衰落的街巷进行活化，在丰富本土餐饮文化内涵的同时激活其生命力，实现老城街巷保护与社会生活的有机结合[2]。

国内目前对餐饮空间布局相关研究较少，现有研究主要对饮食口味、饮食文化差异以及饮食文化的形成成因进行分析[3，4]，缺乏对餐饮在空间上的分析；也有研究针对餐饮类型中的饭店与酒店等空间分布进行分析[5，6]，但主要从旅游服务与经济管理的角度出发。早期研究通过问卷数据获得对餐饮空间的评价，但存在以下不足：样本取样较少，无法全面反映餐饮空间的评价等。随着互联网的快速发展，网络新型数据的发展为餐饮空间研究提供了新的手段和切入点，有学者基于大数据对南京[7]、武汉[8]等城市的餐饮空间格局进

[1] 基金资助: 国家自然科学基金面上项目(编号: 52078217)

行研究，也有学者对广州中心城区餐饮店空间分布进行对比研究[9]，但这类研究空间分析尺度较大，鲜有研究从街巷尺度对城市餐饮空间进行评价与分析[10]。

本文在综合前人的理论与方法基础上，以富含广州特色餐饮文化的老城区作为研究区域，基于其特殊的街巷肌理与空间特点，以街巷为基本研究单位，运用 ArcGIS 平台，结合“美团”数据对广州老城区饮空间进行深度解析。并基于构建多因子综合评价体系分析广州老城街巷餐饮空间分布总体特征，以期挖掘与弘扬广州老城的餐饮地域文化，为广州老城区独特的餐饮空间规划提供参考，促进广州老城区餐饮文化传承与高质量发展。

1 研究对象与方法

1.1 研究区域与对象

本文中广州老城区范围参考《广州历史文化名城保护规划（2021-2035 年）》公示稿中历史城区保护范围(如图 1)[11]，并以该范围内 378 条传统街巷沿线的实体餐饮店为研究对象（如图 2），包括小吃店、饭店、酒楼等以及餐饮老字号等。街巷作为人们生活与活动的重要空间，可视为城市餐饮空间的出发点与发源地，以街巷为尺度对广州老城区的餐饮空间进行研究具有典型性与代表性。

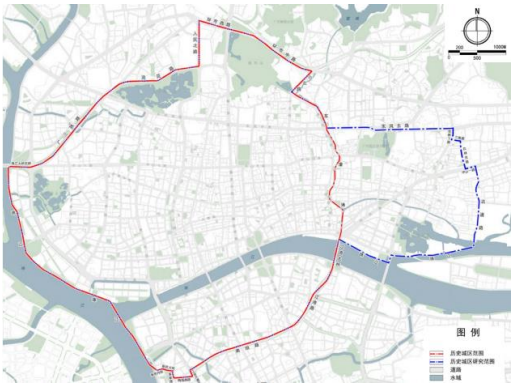

图 1 历史城区保护范围（图源：《广州历史文化名城保护规划（2021-2035 年）》公示稿）

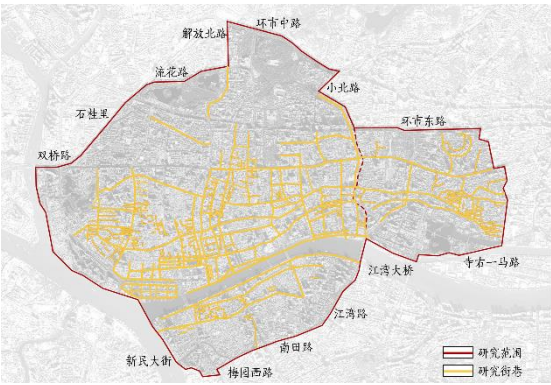

图 2 研究范围与研究对象（图源：自绘）

1.2 研究框架与数据处理

如图 3 所示，分别获取并处理老城区街道路网与美团数据（数据来源如表 1 所示），通过对空间评价指标的分析与指标权重的确定，实现评价体系的构建，以此获得本文所需的广州老城街巷餐饮空间综合评分。

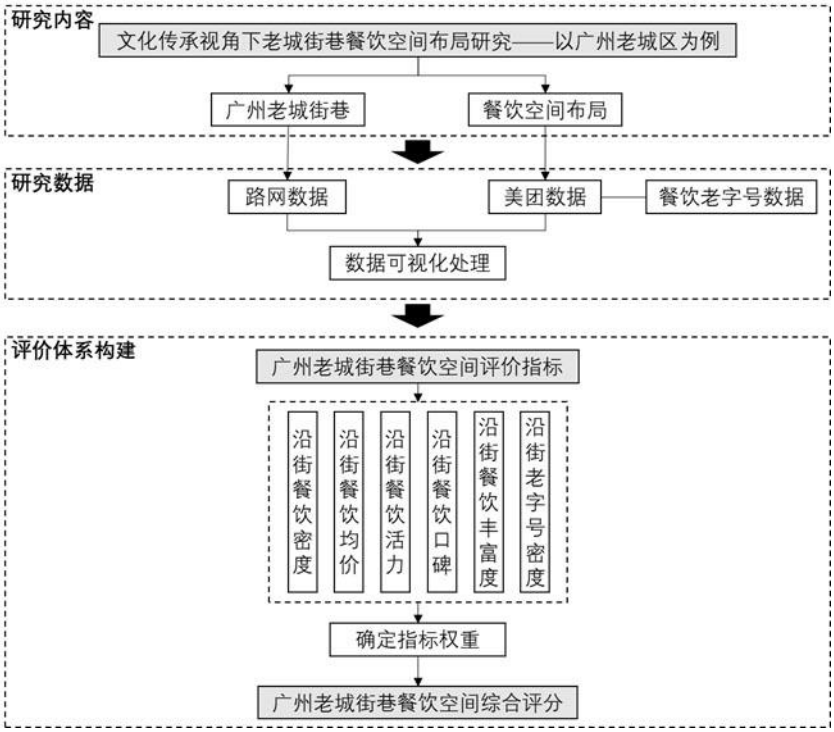

图 3 研究方法框架（图源：自绘）

表 1 数据来源列表

数据	来源
传统街巷数据	具体街巷参考名城公示版本，矢量数据来源于 OpenStreetMap（https://www.openstreetmap.org）
餐饮数据	美团网（https://gz.meituan.com/）
餐饮老字号数据	广州出版社出版的《老广新游之老字号》及网络补充信息整理

对路网数据与餐饮数据分别进行处理，并将两者处理后的结果进行关联与可视化。

（1）路网数据。对路网原始数据进行简化与修正。在 ArcGIS 平台对获取的路网原始数据进行合并与提取，并对道路进行赋值，建立含广州老城区 378 条传统街巷信息的街巷数据库。

（2）餐饮数据。餐饮数据主要为美团数据，餐饮老字号数据是对美团数据的额外补充。

通过利用网络爬虫技术分别以餐饮类型检索和商圈信息检索两种检索方式对美团网网页进行信息爬取，包括坐标信息、评论量、店铺评分、餐饮类型与人均价格等属性信息[12,13]，数据获取时间为 2022 年 11 月，原始数据共计约 7000 家餐饮店。为保证结果的有效性与真实性，对数据进行清洗与预处理，去除重复与位置有误的数据，最终筛选出 5000 余家餐饮店用于本文研究。

同时，老字号能够体现一个城市的地域文化特征与历史痕迹，而餐饮老字号不仅仅是餐饮品牌，更是一种文化景观，能够体现一个城市的餐饮文化深度。为了更深入挖掘广州老城街巷餐饮空间的地域文化特征，本文将上述餐饮店中的餐饮老字号提取出来，作为研究对象之一，最终整理出广州老城区餐饮老字号 27 家，分布情况如图 4 所示[14]。

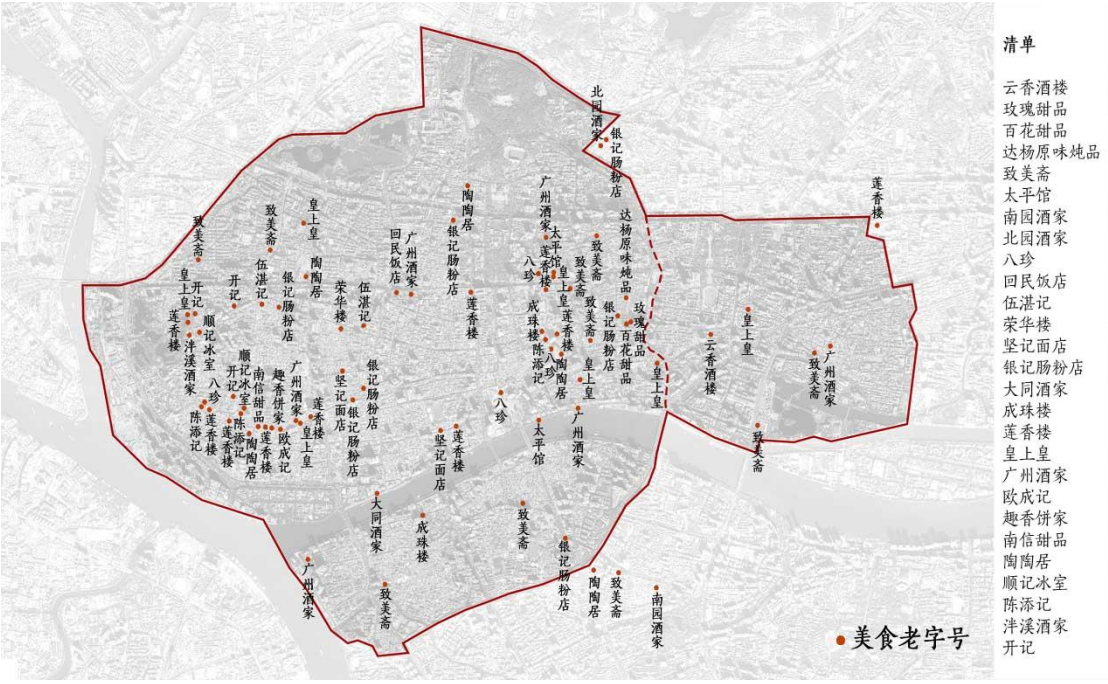

图 4 广州老城区餐饮老字号分布图（图源：自绘）

此外，通过 ArcGIS 对广州老城区街巷餐饮数据进行可视化。将上述得到的含位置信息与指标信息的餐饮数据点在地理地图上标定，输入相关属性数据建立街巷餐饮地理数据库（如图 5）。通过邻近分析将餐饮 POI 数据与路网进行匹配，以便用于后续的数据分析。其中，数据点的搜索半径基于研究相关的餐饮店铺进深与建筑退线确定，为保证数据与街巷线能够较好且较多地匹配，取 20m 为搜索半径进行邻近分析匹配。最终得到餐饮 POI 数据与路网相匹配的广州老城区餐饮店铺分布图（如图 6）。

图 5 街巷餐饮未匹配图（图源：自绘）

图 6 街巷餐饮匹配图（图源：自绘）

2 广州老城街巷餐饮空间综合评价体系构建

将上述含有坐标信息（含广州老城区餐饮老字号）、评论量、店铺评分、餐饮类型、人均价格的餐饮数据进行筛选归类与核密度分析，处理得到沿街餐饮密度、沿街餐饮均价、沿街餐饮活力、沿街餐饮口碑、沿街餐饮丰富度以及沿街老字号密度 6 个评价指标[15]。其中，核密度分析的分类方式为自然间断点分级法，核密度像元大小为 20[16]。

对上述 6 项评价指标分为 5 级进行赋分（如表 2），通过问卷打分形式获取各项指标对应得分，根据打分情况确定不同指标对应的权重，其中，某指标权重=该指标重要性分数/六个数据重要性分数之和。对每条街巷指标分数进行加权求和，获得综合评分。

表 2　广州老城区餐饮评价指标评分标准表

指标名称	指标解释（单位）	指标/分数（5 级）				
		0 分	1 分	2 分	3 分	4 分
沿街餐饮密度	指沿街餐饮 POI 的总数和街巷长度的比值（家/百米）	0-1	1-3	3-5	5-7	＞7
沿街餐饮均价	指沿街餐饮人均价格的平均值（元）	＞80	60-80	40-60	20-40	＜20
沿街餐饮活力	指沿街餐饮评论量的总数和街巷长度的比值（条/米）	1-10	11-20	21-30	31-40	＞40
沿街餐饮口碑	指沿街餐饮评分的平均值（分）	3.0-3.5	3.6-4.0	4.1-4.2	4.3-4.5	4.6-5.0
沿街餐饮丰富度	指沿街餐饮种类的数量（种）	1-3	4-5	6-8	9-10	＞10
沿街老字号密度	指沿街餐饮老字号的数量（家）	1	2	3	4	＞4

3 基于 GIS 核密度分析的广州老城街巷餐饮空间评价

3.1 广州老城街巷餐饮空间分项评价

基于 GIS 核密度分析方法，针对上述六个方面的因子分别进行可视化分析(如图 7 所示)。

图 7-1 沿街餐饮密度图

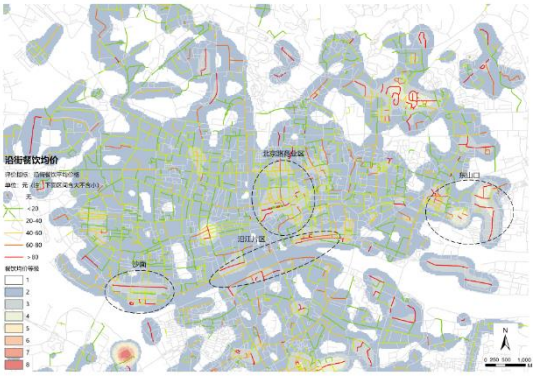

图 7-2 沿街餐饮均价图

图 7-3 沿街餐饮活力图

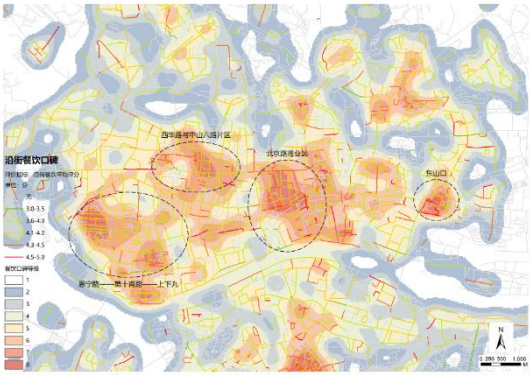

图 7-4 沿街餐饮口碑图

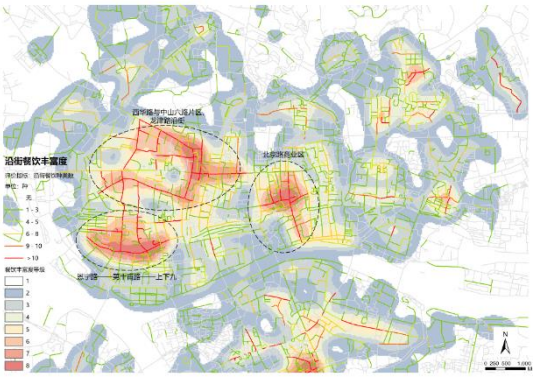

图 7-5 沿街餐饮丰富度图

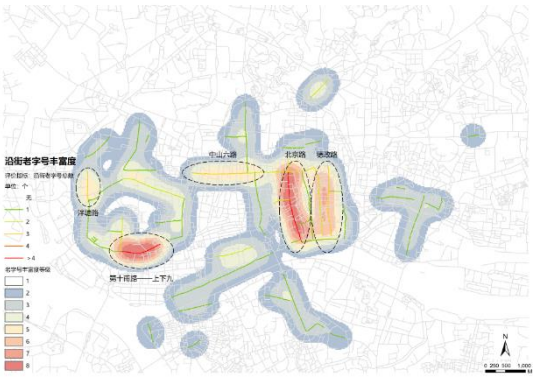

图 7-6 沿街老字号丰富度图

图 7 可视化分析图（图源：自绘）

其中，沿街餐饮密度呈现出一定的区域聚集性特征。如图 7-1 所示，北京路商业片区密度最高，呈现出餐饮密度的高热区，且集聚范围远大于其他区域；西华路与中山六路片区、恩宁路——上下九片区、东山口与东风东路片区呈现出餐饮密度的次热区，但分布范围相对较小且较为分散；海珠区呈现出餐饮密度的低值区域，出现该情况可能与其以居住功能为主有关。

广州老城街巷餐饮价格低于广州中心城区人均价格，由此可初步得到广州老城街巷餐饮整体消费水平较低的结论。如图 7-2 所示，均价较高区域较多存在于沙面片区、北京路商业区、东山口片区、永庆坊等旅游片区以及沿江片区，此类地区因其旅游等功能，具有

较高地租水平，因此均价高于周边区域；同时，均价较高的街巷分布较为分散，在广州老城区各个区域内均有所分布。

沿街餐饮活力呈现一定的区域聚集性特征。同时，广州老城区内沿街餐饮的活力普遍较高，证明老城区整体具有较高的餐饮活力，以老城区作为广州餐饮文化的传承区域具有较高可行性。如图 7-3 所示，西华路与中山六路片区、龙津中路沿街片区、北京路商业区、恩宁路——第十甫路——上下九片区、东山口片区、东风东路片区均呈现较为高的活力，这些片区均为人群聚集密度较高区域，高密度的人群带动了区域的发展，带来了餐饮业的高活力。

广州老城沿街餐饮口碑整体较为平均，口碑较高的街巷整体较为分散，但仍呈现出一定的区域聚集性。如图 7-4 所示，西华路与中山六路片区、恩宁路——第十甫路——上下九片区、北京路商业区、东山口片区呈现口碑的高热聚集区；其中，北京路商业区中的街巷基本呈现出较高的口碑；东山口片区分布较多高等级口碑街巷。

沿街餐饮丰富度呈现较强的区域聚集性，且丰富度较高的街巷较为显著。如图 7-5 所示，西华路与中山六路片区、龙津路沿街片区、恩宁路——第十甫路——上下九片区、北京路商业区均呈现出丰富度的高热值区；其中，西华路与中山六路片区、龙津路沿街片区、恩宁路——第十甫路——上下九片区三个片区沿街丰富度等级高的街巷连续度较高，片区与片区间连续性较强，形成较为完整的高丰富度区域。

广州老城街巷沿街老字号分布较广，于广州老城区各个区域均有分布。如图 7-6 所示，第十甫路——上下九沿街分布密度最高，泮塘路、中山六路、德政路次之；同时，广州餐饮老字号主要分布于老城区骑楼环沿街与北京路商业区，这两个片区发展历史较早，保留较多餐饮老字号。

3.2 广州老城街巷餐饮空间综合评价

本文共获得有效问卷 95 份，问卷所得的分获得权重结果（如表 3）。

表 3 权重结果表

指标	重要性分数	权重百分比
沿街餐饮密度	7.61	17.12%
沿街餐饮均价	7.31	16.44%
沿街餐饮活力	7.39	16.62%
沿街餐饮口碑	8.58	19.32%
沿街餐饮丰富度	7.31	16.44%
沿街老字号密度	6.25	14.06%

对各项指标加权求和所得的综合评分进行排序，可得综合排名前二十的街巷（如表4）。通过对综合评分进行可视化操作，可得街巷综合评分图（如图 8），由图中可以看出综合评分较高的街巷具有较高的集聚性。

对街巷综合评分结果进行核密度分析（如图 9），可发现广州老城街巷各高水平聚集餐饮空间的分布呈现出东西向轴线分布的特征，其中，西华路与中山六路片区、恩宁路——第十甫路——上下九片区、北京路商业区呈现出较高水平餐饮的聚集，形成一定区域范围的美食圈，东山口片区相较次之。同时，历史价值意义显著的区域（如骑楼环、北京路等），往往呈现出与其历史背景相应的更高的餐饮水平，可推测其与广府传统美食的传承有关。

表 4 综合排名前二十街巷表

排名	街巷名称	综合评分	口碑等级	丰富度等级	活力等级	密度等级	均价等级	老字号等级
1	北京路	3.4492	2	4	4	4	3	4
2	下九路	3.4204	1	4	4	4	4	4
3	恩宁路	3.0274	2	4	4	4	3	1
4	龙津中路	2.9968	2	4	4	3	3	2
5	署前路	2.8868	2	4	4	4	3	0
6	大沙头三马路	2.8580	1	4	4	4	4	0
7	龙津西路(东西向)	2.8494	2	4	4	2	4	1
8	龙津东路	2.8256	2	4	4	2	3	2
9	中山六路	2.7730	1	4	4	2	3	3
10	永庆一巷	2.7206	3	1	4	3	4	1
11	金花直街	2.7206	2	3	3	4	4	0
12	龙源新街	2.7156	2	4	4	3	3	0
13	小梅大街	2.6936	1	4	4	4	3	0
14	恩洲大巷	2.6868	1	4	4	3	4	0
15	东华西路	2.6630	1	4	4	3	3	1

16	同福东路	2.6562	1	4	4	2	4	1
17	宝华路	2.6544	2	4	4	1	3	2
18	宝源路	2.5580	2	3	4	4	2	0
19	和安街	2.5512	2	2	4	3	4	0
20	西华路	2.5444	2	4	4	2	3	0

图 8 街巷综合评分图（图源：自绘）

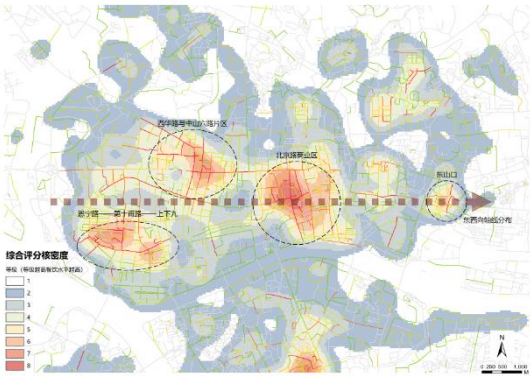

图 9 街巷综合评分核密度图（图源：自绘）

根据大数据的综合评价分析结果，结合实际情况对广州老城街巷的总体布局与交通现状进行分析。

结合广州老城区的街巷总体分布格局进行分析（如图 10），发现餐饮街巷主要集中在四个片区：北京路综合文旅区、东山口中西融合区、老西关传统小吃区、西华路老广风味区，并形成以北京路为核心，东山口、老西关、光孝寺为主要节点，宝华路、西华路、东华路等为主要联系纽带的“一核一廊多带多节点”的美食街巷分布格局。

结合广州老城区的交通现状（如图 11），由于公众出行在很大程度上依赖于轨道交通，分析发现老城区美食街巷的集中区域往往也是轨道交通站点布局的位置。主要涉及到的轨道交通线路有：1 号线、2 号线、6 号线、8 号线。主要涉及站点有：东山口、北京路、公园前、西门口、陈家祠、彩虹桥、长寿路、黄沙。这些站点大多数人流量较大，与附近的餐饮街巷可达性较高，可较好服务于游客，与步行游玩的出行方式有较好的衔接。

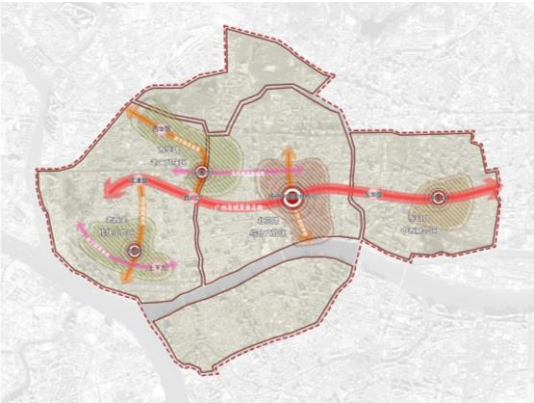

图 10 街巷总体分布格局图（图源：自绘）

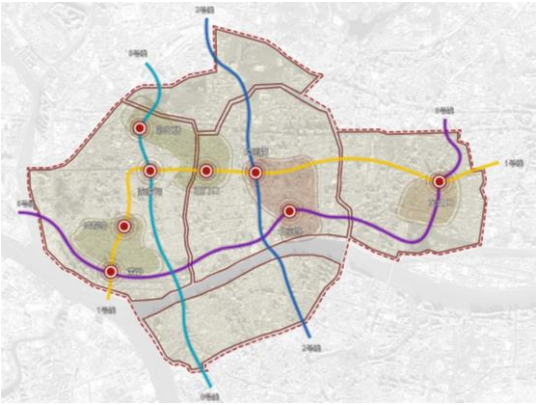

图 11 广州老城区交通现状图（图源：自绘）

4 广州老城街巷餐饮空间优化提升对策

广州老城街巷餐饮空间具有浓郁的餐饮文化特色以及独特的生活气息，但随着城市化的推进，老城区内越来越多的街巷走向衰落，通过对文化的注入与传承以及餐饮空间的针对性规划，实现街巷活力的恢复与延续，有助于广州老城区餐饮文化传承与高质量发展.建议通过发挥餐饮老字号优势、构建老城特色游径、策划多元特色餐饮消费，实施点-线-面三个层面下的广州老城街巷餐饮空间规划策略。

4.1 以点带面，充分发挥餐饮老字号优势实施针对性导则设计

实施针对性的导则设计为餐饮老字号的生存提供保护与帮助，有助于充分展示极具广州特色的城市市井文化。广州老城区分布了广州大多数的餐饮老字号(如图 12)，这些餐饮老字号的发展与生存有助于广州多元文化与餐饮文脉的传承，但由于广州老城区各项保护导则的限制，餐饮老字号处于极大困境中。可实施针对性导则，即在保证不破坏历史风貌协调性与各项安全规范的前提下，放宽对餐饮老字号的限制，提出针对餐饮老字号特点的导则设计，既要考虑餐饮街巷的步行街特征，同时应区分其与其它餐饮店铺的不同，可分别从建筑色彩材料、广告、立面绿化等进行导则设计。同时鼓励各类餐饮老字号入驻街巷，鼓励文化+餐饮多元模式如戏曲+餐饮、茶文化+餐饮等，为街巷提供文化底蕴与人气，以餐饮老字号为核心点带动街巷的发展[17]。



图 12 广州网红餐饮老字号照片（图源：网络）

4.2 以线带面，通过特色餐饮游径彰显广州美食之都文化特色

结合综合评价结果，以老城街巷餐饮空间布局为基础，考虑游客不同的游览体验需求以及步行可达性，可设计广州老城特色餐饮游径以将餐饮文化融入到旅游中，如图 13 所示：（一）串联西华路、光孝寺、西门口、龙津路、宝华路、恩宁路的市井烟火气息体验游径，该游径所涉区域沿街餐饮丰富度与活力较高，区域内历史与建筑保留完善、餐饮文化保存程度高，可供游客体验最具广府特色的餐饮文化；（二）串联北京路、文明路、东华路、东山口的纵享精选品质打卡游径，该游径以传统中轴核心与东山口为两处关键核心点，区域内沿街餐饮活力、口碑以及沿街老字号丰富度均处于较高水平，同时区域内兼具旅游、购物功能，打造旅游餐饮一体化游径。

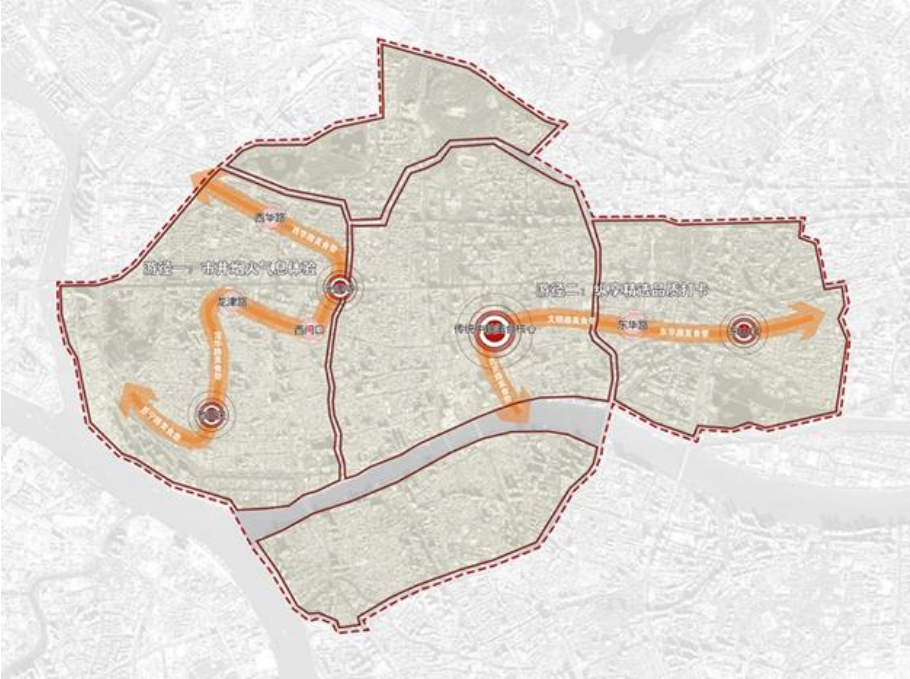

图 13 特色餐饮游径示意图（图源：自绘）

4.3 结合街巷餐饮空间分项评价策划多元特色餐饮消费

通过对 6 项指标进行分析，对不同片区的核心竞争力策划针对性的餐饮特色活动，如餐饮均价较低的街巷以其价格低为卖点，策划免费体验品尝等活动，以此增加其人群聚集活力并打出口碑；餐饮口碑较高的街巷可策划美食打卡活动，带动街巷的整体活力。同时，街巷与街巷之间、片区与片区之间可以通过特色餐饮消费形成更为紧密互补的餐饮体验带，由餐饮老字号密度高以及餐饮口碑较高的街巷作为核心街巷，带动周围的街巷，通过活动策划打造高品质高活力的餐饮文化片区。

5 结论与讨论

本文以文化传承视角对广州老城的餐饮空间从街巷尺度进行多角度与综合评价，并针对评价提出能够实现广州老城街巷文化注入与活力提升的相应空间规划策略。通过研究发现：1）广州老城街巷餐饮空间存在一定的区域聚集性与区别于中心城区的特征。其中，沿街餐饮密度、活力与丰富度呈现出一定的区域聚集性特征；老城街巷餐饮整体消费较低；沿街餐饮口碑整体较为平均，口碑较高的片区呈现出一定的区域聚集性；2）老字号能够体现一个城市的地域文化特征与历史痕迹，而餐饮老字号能够体现一个城市的餐饮文化深度。广州老城街巷沿街老字号分布较广，老城区内各个区域均有所分布，对老城区的街巷餐饮发展具有带动作用。3）广州老城街巷各高水平聚集餐饮区的分布呈现出东西向轴线布局的特征，该结果与广州老城区的总体布局和交通现状存在密切联系，餐饮街巷热点主要集中分布在四个片区：北京路综合文旅区、东山口中西融合区、老西关传统小吃区、西华路老广风味区，且集中区域往往布局于轨道交通站点周边。

本研究还存在一定局限性。虽然基于大数据的餐饮信息具有数据量大、时效性强的特点，能在一定程度上完整准确地反映出城市餐饮店的空间特征，但仍存在数据精度和准确度可能存在一定偏差的局限性，后续研究期望可通过持续追踪老城街巷餐饮空间信息，探索不同时空尺度的老城街巷餐饮空间特征，进一步挖掘与弘扬广州老城独特的餐饮地域文化，为进一步彰显美食广州美丽和文化传承助力。

参考文献

[1] 舒舍玉,王润,孙艳伟,刘健,肖黎姗.城市餐饮业的空间格局及影响因素分析——以厦门市为例[J].热带地理,2012,32(02):134-140.

[2] 陈楠,夏青,刘立钧.文化传承视角下的历史街巷业态构成分析——以天津市古文化街为例[J].天津城建大学学报,2016,22(06):393-400.

[3] 陈传康．中国饮食文化的区域分化和发展趋势[J]．地理学报，1994，49（3）：226-235.

[4] 蔡晓梅，甘巧林，张朝枝．广州饮食文化景观的空间特征及其形成 机理分析[J]．社会科学家，2004，106（2）：95-98.

[5] 胡志毅，张兆干．城市饭店的空间布局分析——以南京市为例[J]．经济地理，2002，22（1）：106-110.
[6] 袁小红，毛端谦，刘婕．城市星级饭店空间分布模式分析——以南昌市为例[J]．江西师范大学学报：自然科学版，2010，34（3）：325-330.
[7] 张旭，徐逸伦．南京市餐饮设施空间分布及其影响因素研究[J]．热带地理，2009，29（4）：362-367.
[8] 杜晓初,李中元,陈潇.基于点评数据的武汉市餐饮发展水平空间差异[J].地理科学,2021,41(08):1389-1397.
[9] 莫惠斌,罗珂,王少剑,周春山.广州市中心城区餐饮店空间分异与机制差异研究——基于传统店与外卖店的对比[J].地理研究,2022,41(12):3318-3334.
[10] 梁璐.城市餐饮业的空间格局及其影响因素分析——以西安市为例[J].西北大学学报(自然科学版),2007(06):925-930.
[11] 《广州历史文化名城保护规划（2021-2035 年）》公示稿.
[12] 秦萧,甄峰,朱寿佳,席广亮.基于网络口碑度的南京城区餐饮业空间分布格局研究——以大众点评网为例[J].地理科学,2014,34(07):810-817.
[13] 徐晓宇,李梅.基于开源大数据的北京地区餐饮业空间分布格局[J].地球信息科学学报,2019,21(02):215-225.
[14] 周爱华,张远索,付晓,朱海勇,董恒年.北京城区餐饮老字号空间格局及其影响因素研究[J].世界地理研究,2015,24(01):150-158.
[15] 陈晓东.基于街道尺度的北京二环内餐饮业活力及影响因素分析[J].北京规划建设,2020(01):11-16.
[16] 单欣,徐坚,刘映晞,隋心,何雄.基于 POI 数据的昆明中心城区餐饮业空间分布格局研究[J].昆明理工大学学报(自然科学版),2019,44(05):115-120.
[17] 陶鸿,赵媛,袁晓燕,陶萍.南京“老字号”餐饮企业地理区位变化及影响因素分析[J].世界地理研究,2011,20(03):145-154.